ROYAUME DU MAROC
WILAYA DE LA REGION CASABLANCA SETTAT
PROVINCE DE BENSLIMANE
COMMUNE EL MANSOURIA

PROJET :

"EBLA ONE"

CONSTRUCTION D'UNE RESIDENCE BALNEAIRE
A REZ DE CHAUSSEE + 3 ETAGES
AVEC PARKING AU SOUS SOL

SIS : LOT 16 LOTISSEMENT JAWHARAT
AL BAHR I

ETUDE :

- MASSE BALCON
- ETAGE COURANT
- FACADES- COUPE

N°PLAN 1/2

MAITRE D'OUVRAGE: ELBA ONE SARL
Representée par
Mr ABDELOUAHED AMEZIANE

N° TITRE FANCIER	SURFACE
TF 36089/25	1h18a41ca

ARCHITECTE : EL ATOUANI MOHAMMED AMINE
ARCHITECTE DESA
Villa des arts et métiers ,Lot. SANIA,Bd. Hassan II ,MOHAMMEDIA
Tél: 05 - 23 - 31 - 53 - 49 / Fax : 05 -23 - 31 - 53 - 62

DATE ORIGINE	ECHELLE
01/04/2024	1/200

BUREAU D'ETUDE : Société SYNERGIE Topo (SARL) des travaux topographiques
Ingénieur Géomètre Topographe : TREYI Ouissal
Adresse: N°41 App N°4 Imm ELAYADI Bd Hassan II-Benslimane
Téléphone : 05 23 29 82 13
GSM :06 28 68 90 53
E-mail :synergie.topo@gmail.com

Cadre Réservé à L'administration	Ind	Rev	Remarque	Date
				13/05/2024
				19/05/2024
			MODIFICATION DES TERRASSE	25/06/2024

L'architecte sousigné, s'engage à surveiller les travaux jusqu'à l'otention du permis d'habiter,l'architecte doit être averti 48H avant tout commencement des travaux
Le propriétaire et l'entrepreneur s'engagent de présenter un plan B.A. fait par un ingénieur agrée.

EMETTEUR	DESSINE PAR :	VISE PAR :
EL ATOUANI MOHAMED AMINE ARCHITECTE DESA		

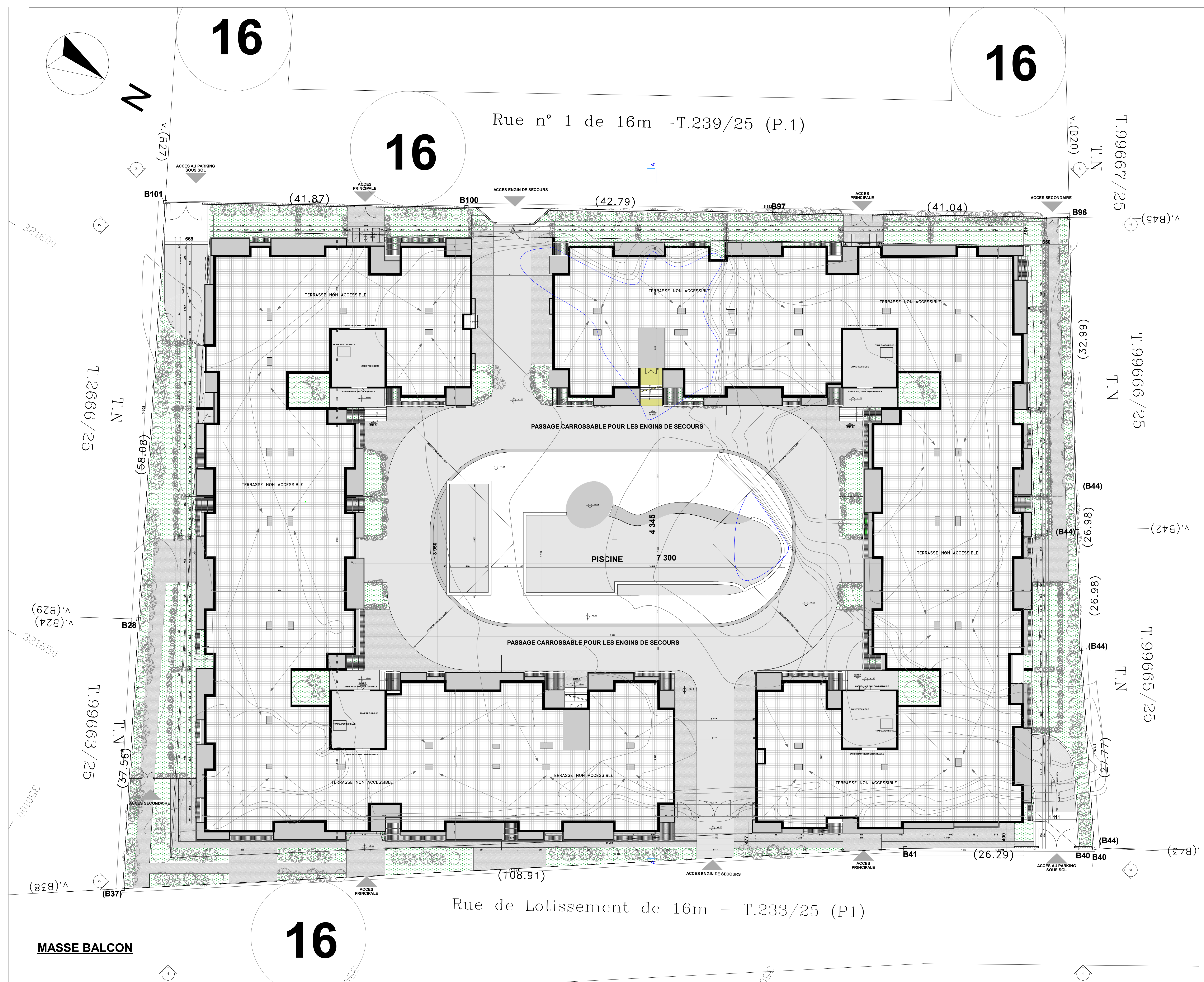
16
16
16
16
N
Rue n° 1 de 16m -T.239/25 (P.1)
Rue de Lotissement de 16m - T.233/25 (P1)
T.99667/25
T.99666/25
T.99665/25
T.99663/25
T.2666/25
T.N
(41.87)
(42.79)
(41.04)
(32.99)
(26.98)
(27.77)
(26.29)
(108.91)
(58.08)
(37.56)
B101
B100
B97
B96
B44
B40
B41
B37
B28
v.(B27)
v.(B20)
v.(B45)
v.(B42)
v.(B43)
v.(B29)
v.(B24)
v.(B38)
ACCES AU PARKING SOUS SOL
ACCES PRINCIPALE
ACCES ENGIN DE SECOURS
ACCES SECONDAIRE
TERRASSE NON ACCESSIBLE
PASSAGE CARROSSABLE POUR LES ENGINS DE SECOURS
PISCINE
7 300
4 345
3 950

MASSE BALCON

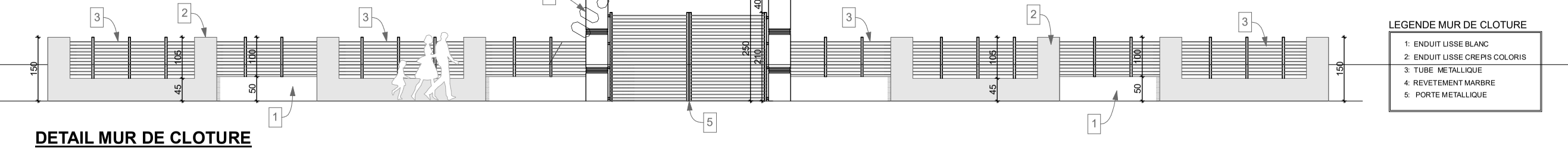

DETAIL MUR DE CLOTURE

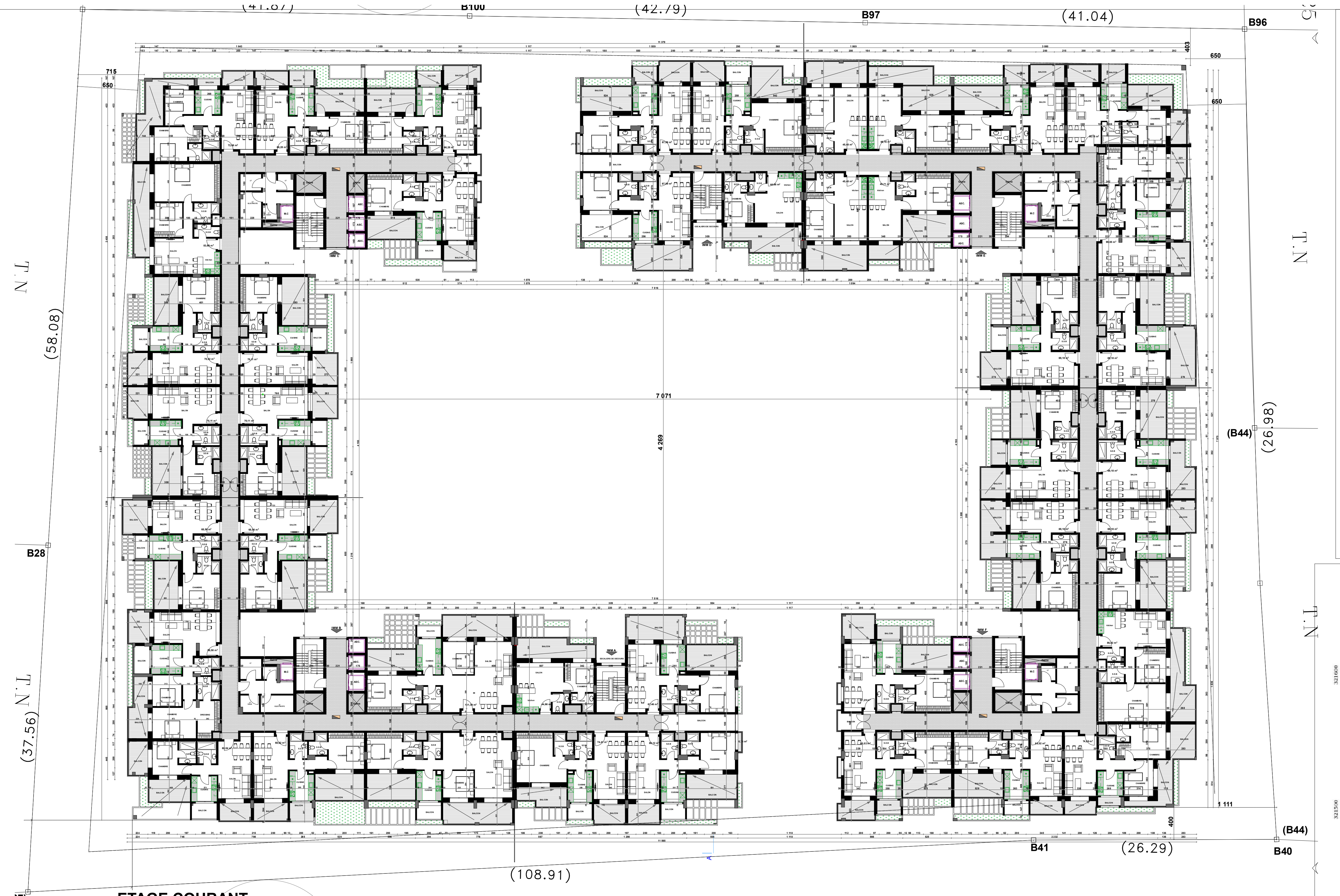
B100
B97
B96
B28
B41
B40
(B44)
(41.87)
(42.79)
(41.04)
(58.08)
(37.56)
(26.98)
(26.29)
(108.91)
T.N

ETAGE COURANT

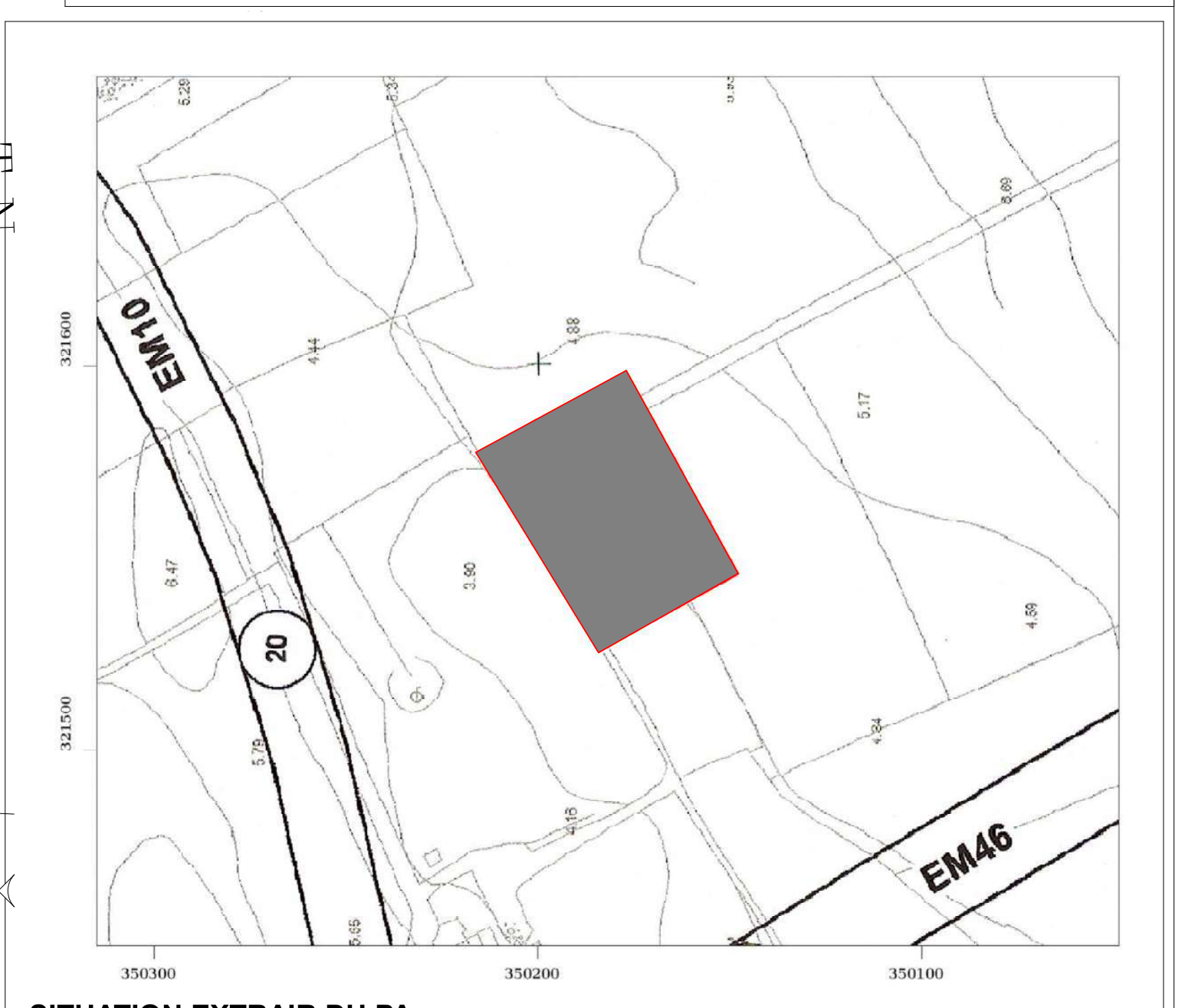
EM10
EM46
20

SITUATION EXTRAIT DU PA

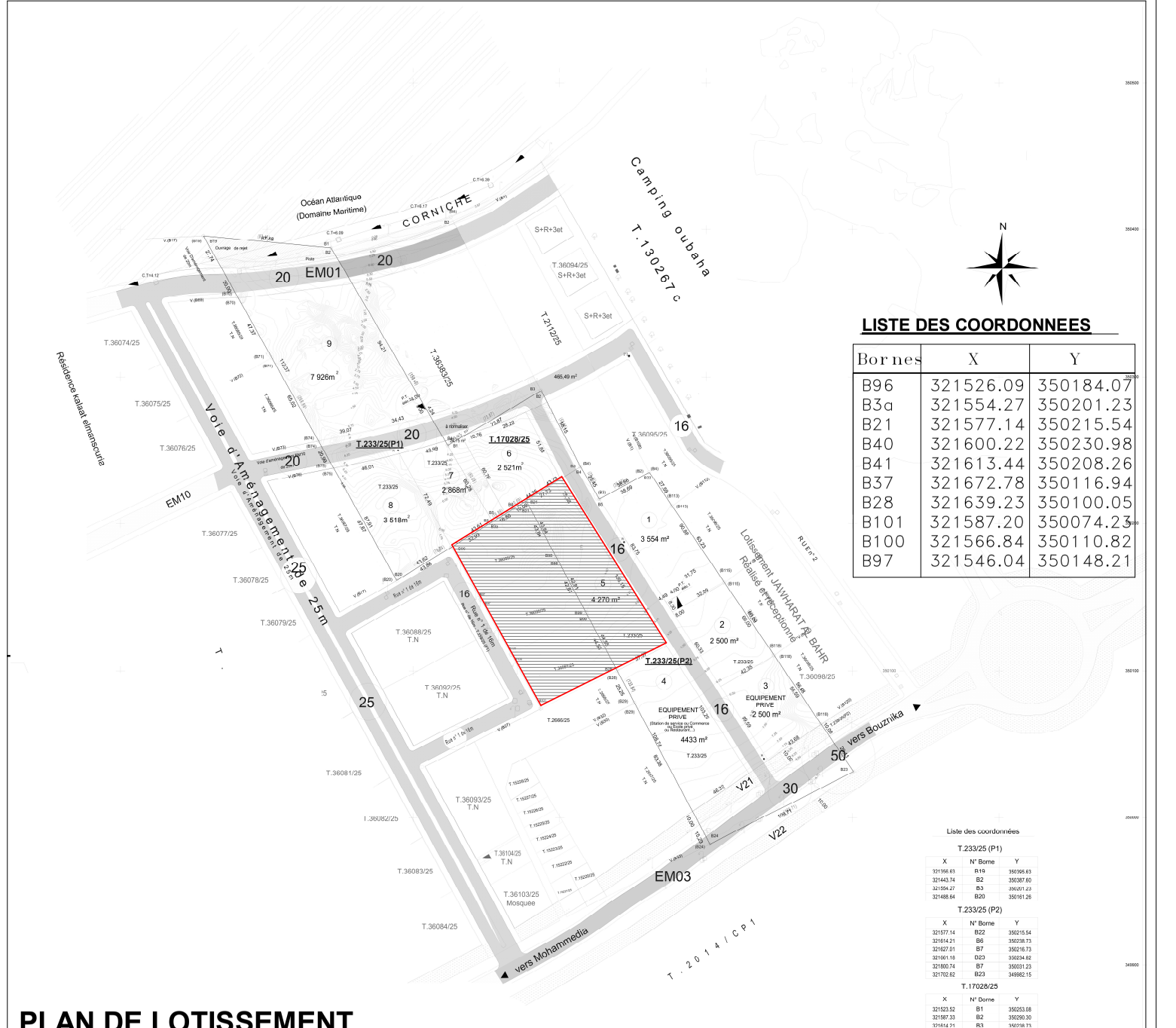
Camping oubaha
T.130267c
N
16
30
50
V21
V22
EM03
vers Bouznika
vers Mohammedia
Lotissement JAWHARAT AL BAHR
Réalisé et réceptionné
RUE n° 2
EQUIPEMENT PRIVE
3 554 m²
2 500 m²
4433 m²
T.233/25(P2)
T.36098/25
T.36095/25

LISTE DES COORDONNEES

Bornes	X	Y
B96	321526.09	350184.07
B3a	321554.27	350201.23
B21	321577.14	350215.54
B40	321600.22	350230.98
B41	321613.44	350208.26
B37	321672.78	350116.94
B28	321639.23	350100.05
B101	321587.20	350074.23
B100	321566.84	350110.82
B97	321546.04	350148.21

PLAN DE LOTISSEMENT

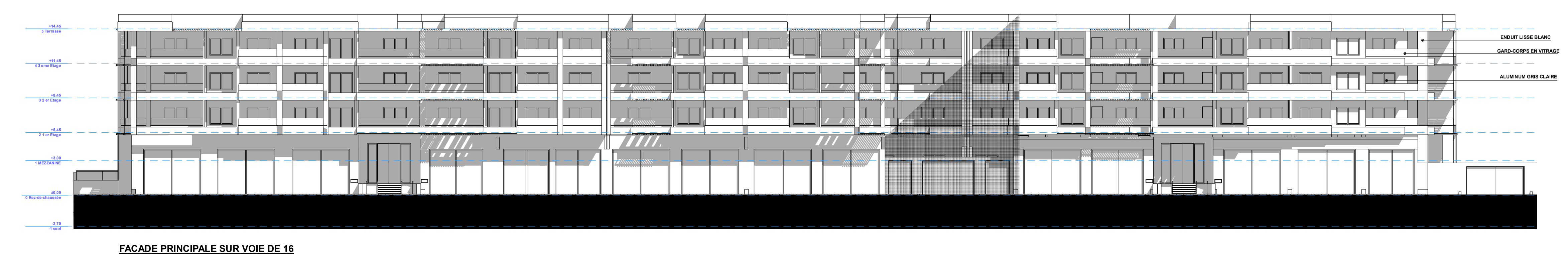
ENDUIT LISSE BLANC
GARDE-CORPS EN VITRAGE
ALUMINIUM GRIS CLAIRE

FACADE PRINCIPALE SUR VOIE DE 16

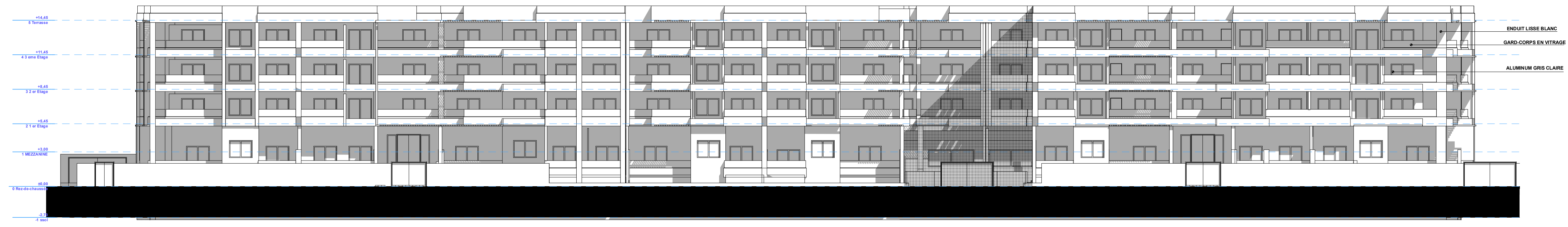
ENDUIT LISSE BLANC
GARDE-CORPS EN VITRAGE
ALUMINIUM GRIS CLAIRE

FACADE ARRIERE

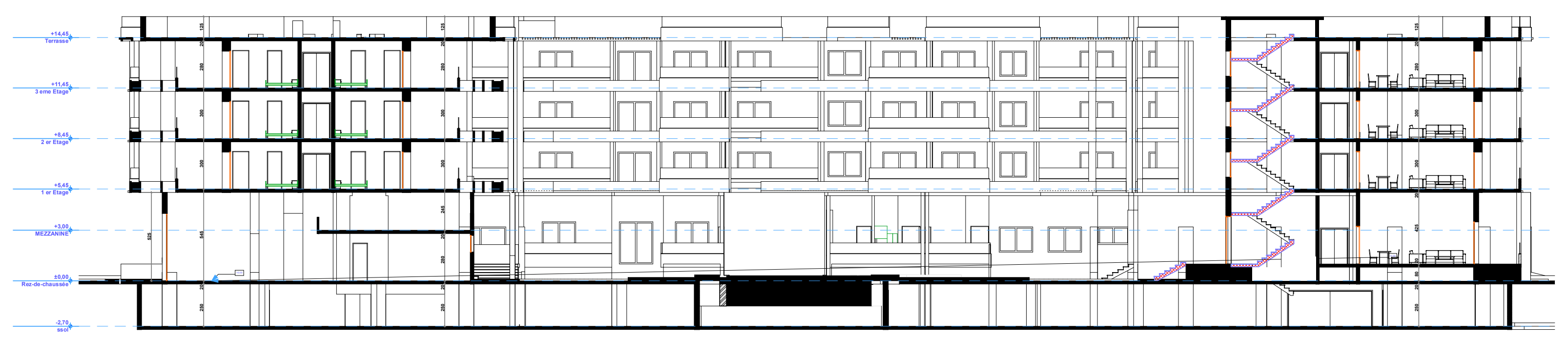

COUPE A-A

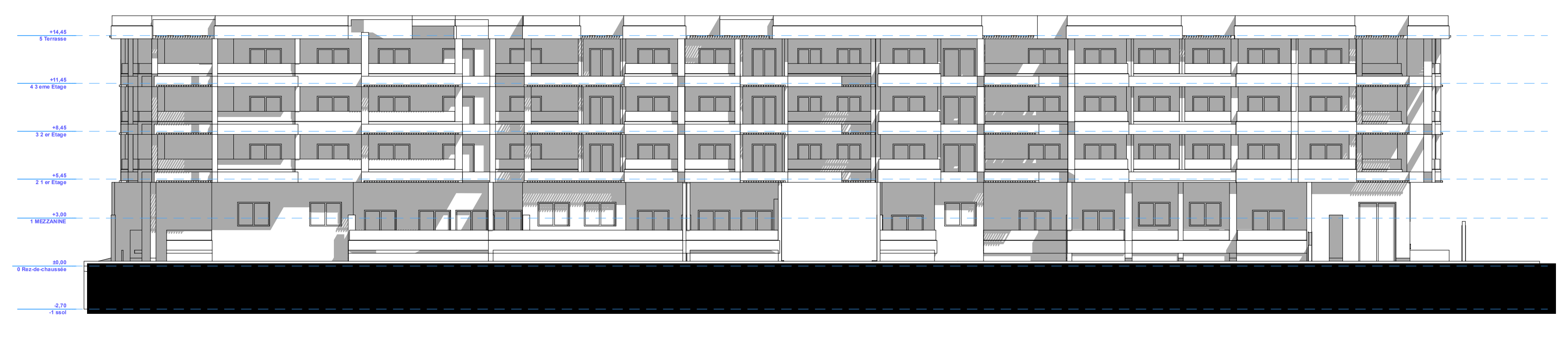
ENDUIT LISSE BLANC
GARDE-CORPS EN VITRAGE
ALUMINIUM GRIS CLAIRE
PERGOLA EN BOIS

FACADE LATERALE GAUCHE

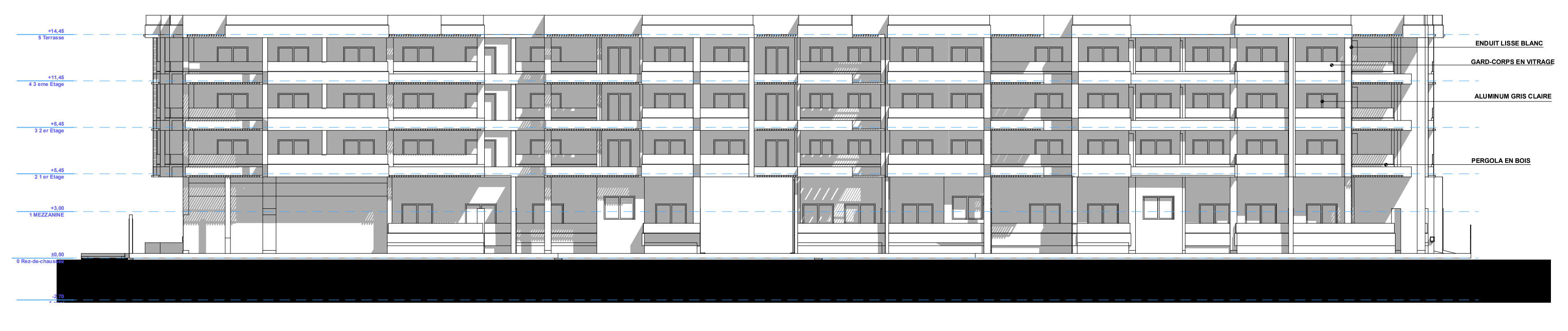

FACADE LATERALE DROITE

TABLEAU QUANTITATIF

IMMEUBLE	Nbr MAGASIN	Nbr Appt au RDC	Nbr Appt PAR ETAGE	TOTAL MAGASIN PAR IMMEUBLE	TOTAL APPARTEMENTS PAR IMMEUBLE
A	3	0	4	3	12
B	3	4	7	3	25
C	0	10	9	0	37
D	0	4	4	0	16
E	0	9	11	0	42
F	3	3	9	3	30
TOTAL	9	30	44	9	162

NOMBRE DE PLACE DE PARKING AU SOUS SOL 230 PLACES

SURFACE CONSTRUITE

NIVEAUX	SURFACE CONSTRUITE
SOUS SOL	7500 m²
REZ DE CHAUSSEE	4080 m²
1er ETAGE	3400m²
2éme ETAGE	3400m²
3éme ETAGE	3400m²
TOTAL	21780m²

SURFACE TERRAIN 11841 m²

SURFACE CONSTRUITE AU SOL 4080 m²

SURFACE PLANCHERS SANS SOUS SOL 14280m²

Lu et approuvé
Signé par TREYI OUISSAL
à BENSLIMANE
le 08/07/2024

Lu et Approvè
Signé par NADYA LEKHEL
à Mohammadia
le 23/07/2024

LU ET APPROUVE
Signé par EL ATOUANI MOHAMMED AMINE
à MOHAMMEDIA
le 23/07/2024

LU ET APPROUVE
Sign par OUBAHA FAYCAL
COMMUNE EL MANSOURIA
le 23/11/2024

ROYAUME DU MAROC
WILAYA DE LA REGION CASABLANCA SETTAT
PROVINCE DE BENSLIMANE
COMMUNE EL MANSOURIA

PROJET :
"EBLA ONE"
CONSTRUCTION D'UNE RESIDENCE BALNEAIRE
A REZ DE CHAUSSEE + 3 ETAGES
AVEC PARKING AU SOUS SOL
SIS : LOT 16 LOTISSEMENT JAWHARAT
AL BAHR I

ETUDE :
- SOUS SOL
- REZ DE CHAUSSEE
- SOUPENTE

N°PLAN 2/2

MAITRE D'OUVRAGE:
ELBA ONE SARL
Representée par
Mr ABDELOUAHED AMEZIANE

N° TITRE FANCIER	SURFACE
TF 36089/25	1h18a41ca

ARCHITECTE :
EL ATOUANI MOHAMMED AMINE
ARCHITECTE DESA
Villa des arts et métiers ,Lot. SANIA,Bd. Hassan II ,MOHAMMEDIA
Tél: 05 - 23 - 31 - 53 - 49 / Fax : 05 -23 - 31 - 53 - 62

DATE ORIGINE	ECHELLE
01/04/2024	1/200

BUREAU D'ETUDE :
Société SYNERGIE Topo (SARL) des travaux topographiques
Ingénieur Géomètre Topographe : TREYI Ouissal
Adresse: N°41 App N°4 Imm ELAYADI Bd Hassan II-Benslimane
Téléphone : 05 23 29 82 13
GSM :06 28 68 90 53
E-mail :synergie.topo@gmail.com

Cadre Réservé à L'administration	Ind	Rev	Remarque	Date
				13/05/2024
				19/05/2024
			MODIFICATION DES TERRASSE	25/06/2024

L'architecte sousigné, s'engage à surveiller les travaux jusqu'à l'otention du permis d'habiter,l'architecte doit être averti 48H avant tout commencement des travaux
Le propriétaire et l'entrepreneur s'engagent de présenter un plan B.A. fait par un ingénieur agrée.

EMETTEUR	DESSINE PAR :	VISE PAR :
EL ATOUANI MOHAMED AMINE ARCHITECTE DESA		

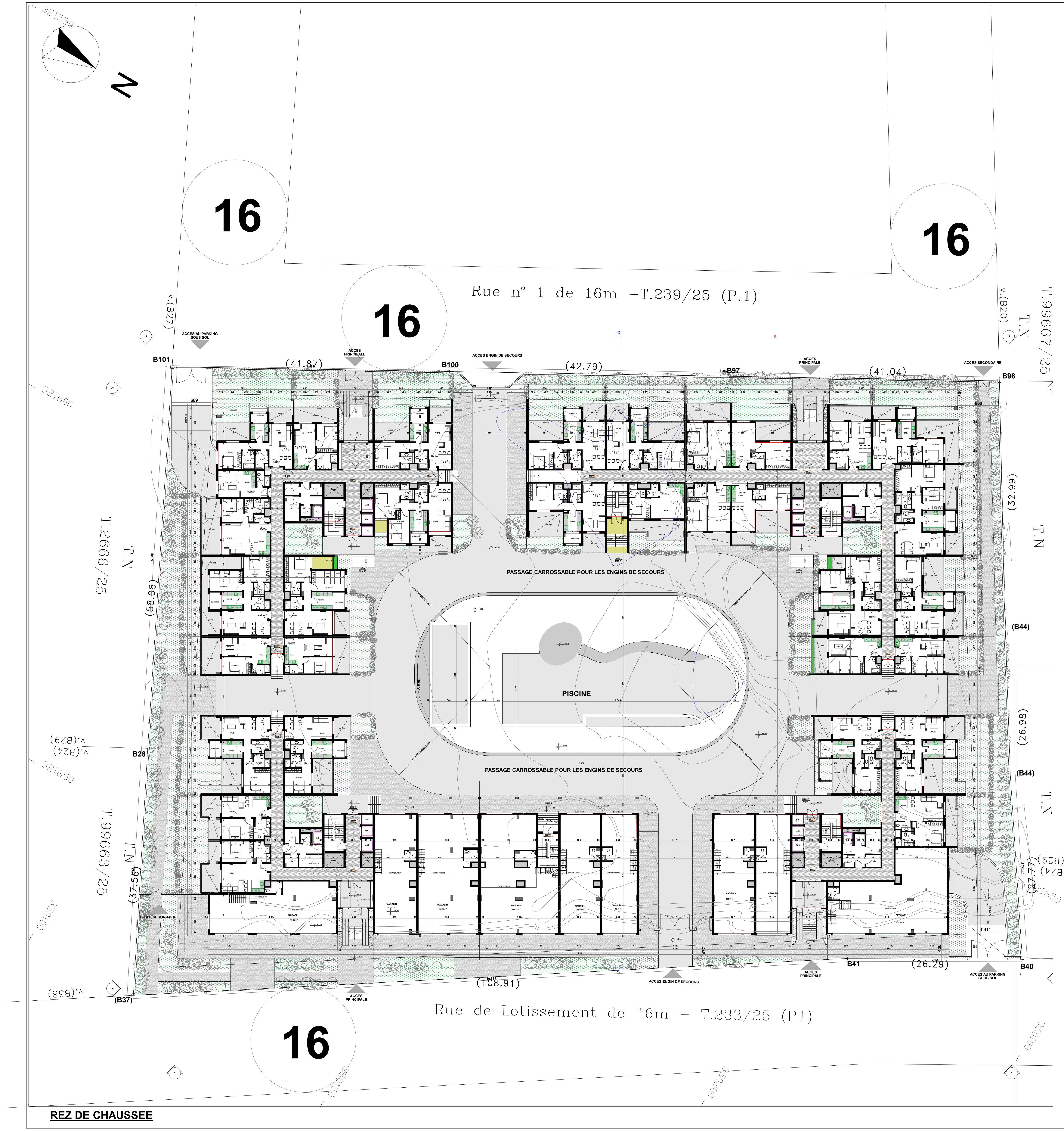
Rue n° 1 de 16m -T.239/25 (P.1)
Rue de Lotissement de 16m - T.233/25 (P1)
16
PASSAGE CARROSSABLE POUR LES ENGINS DE SECOURS
PISCINE
ACCES PRINCIPALE
ACCES SECONDAIRE
ACCES ENGIN DE SECOURS
ACCES AU PARKING SOUS SOL
T.2666/25
T.99663/25
T.99667/25
T.N
B101
B100
B97
B96
B40
B41
B28
B37
(41.87)
(42.79)
(41.04)
(58.08)
(37.56)
(108.91)
(26.29)
(26.98)
(32.99)
N

REZ DE CHAUSSEE

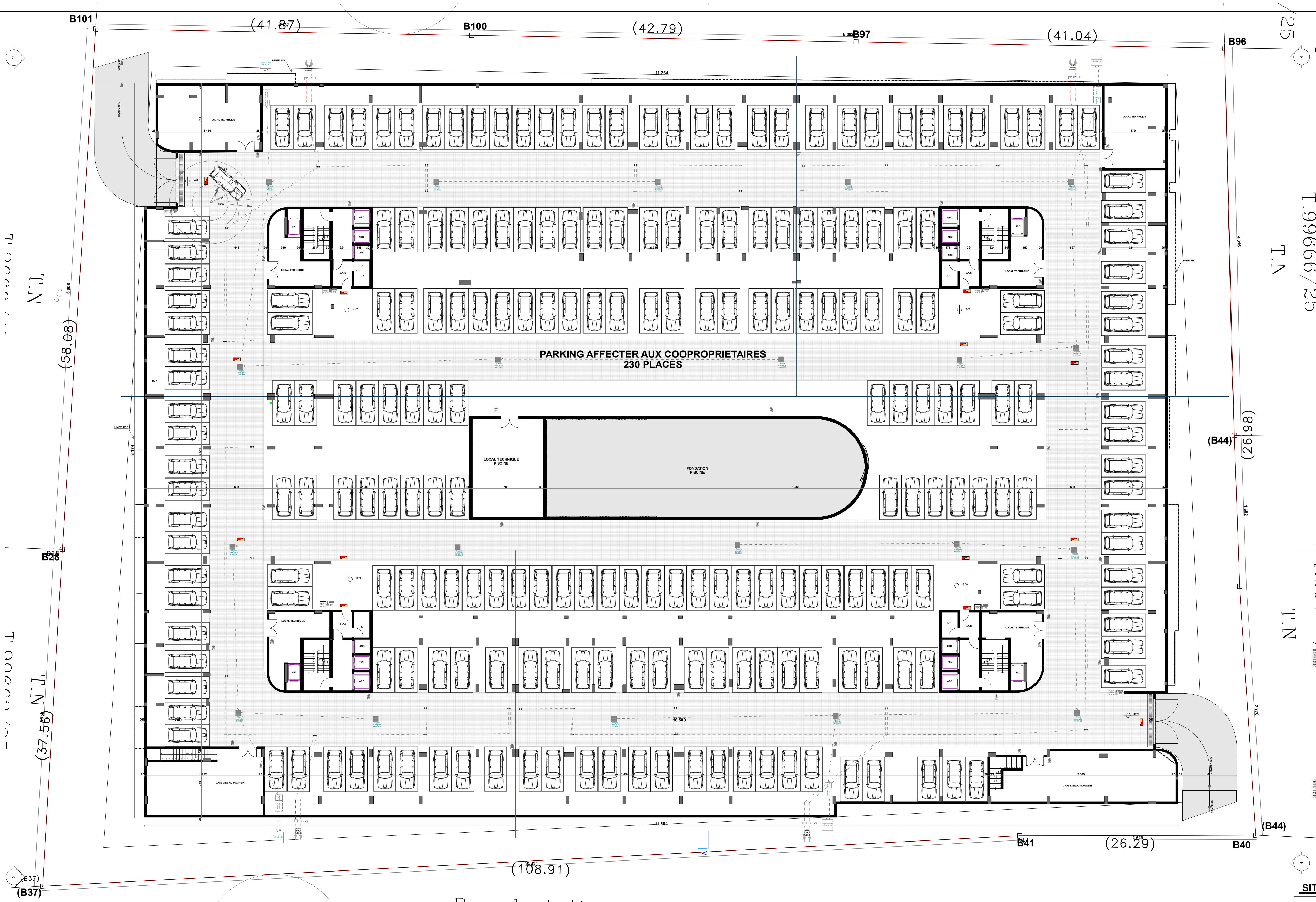
PARKING AFFECTER AUX COOPROPRIETAIRES
230 PLACES
LOCAL TECHNIQUE PISCINE
FONDATION PISCINE
T.99666/25
T.N
B101
B100
B97
B96
B28
B37
B41
B40
(B44)
(41.87)
(42.79)
(41.04)
(58.08)
(37.56)
(108.91)
(26.29)
(26.98)

SOUS SOL

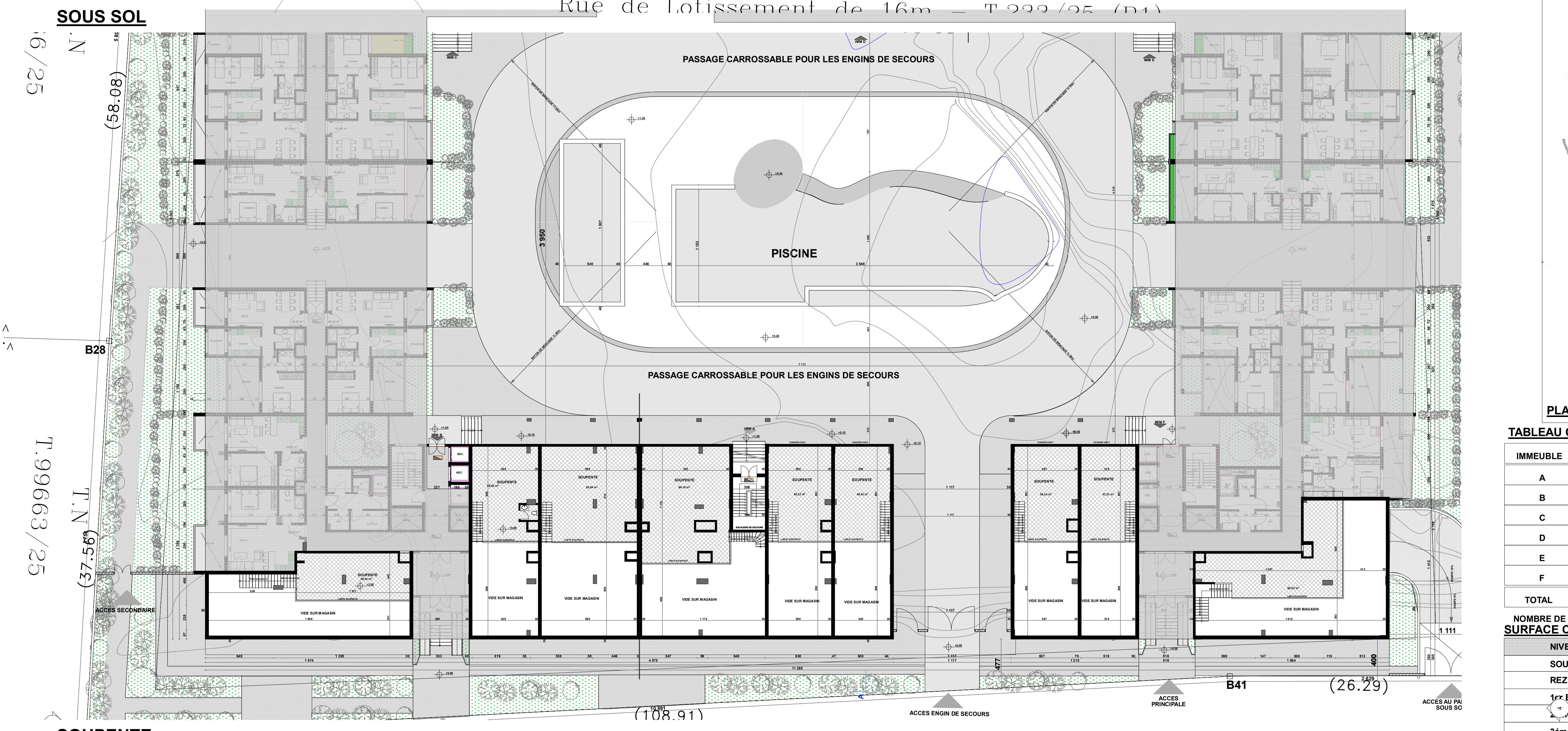
Rue de Lotissement de 16m - T.233/25 (P1)
PASSAGE CARROSSABLE POUR LES ENGINS DE SECOURS
PISCINE
ACCES SECONDAIRE
ACCES ENGIN DE SECOURS
ACCES PRINCIPALE
T.99663/25
T.N
B28
B41
(58.08)
(37.56)
(108.91)
(26.29)

SOUPENTE

EM10
EM46
T.N

SITUATION EXTRAIT DU PA

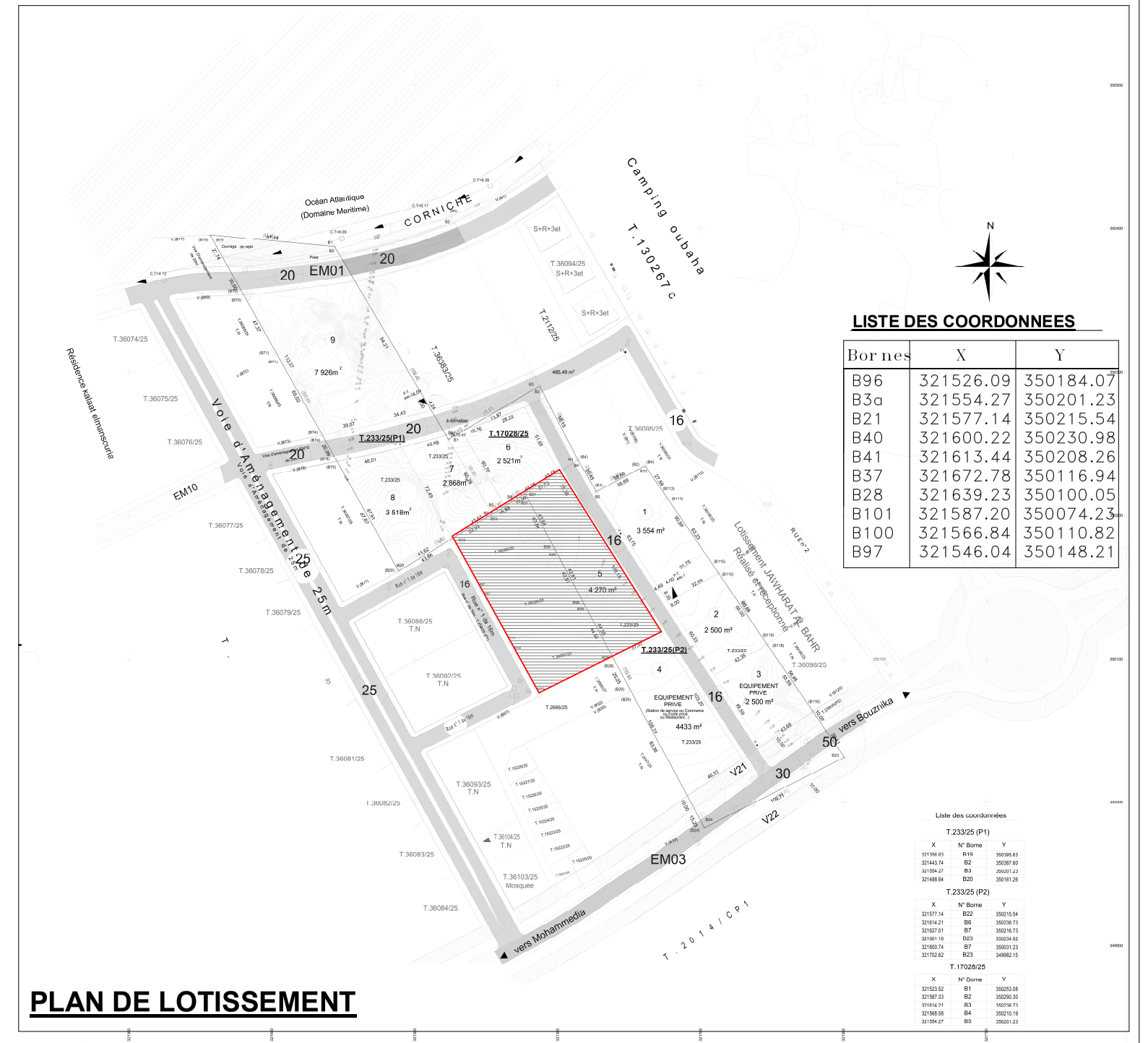
Camping oubaha
T.130267c
Lotissement JAWHARAT AL BAHR
Réalisé et réceptionné
RUE n°2
vers Bouznika
vers Mohammedia
EQUIPEMENT PRIVE
16
N

LISTE DES COORDONNEES

Bornes	X	Y
B96	321526.09	350184.07
B3a	321554.27	350201.23
B21	321577.14	350215.54
B40	321600.22	350230.98
B41	321613.44	350208.26
B37	321672.78	350116.94
B28	321639.23	350100.05
B101	321587.20	350074.23
B100	321566.84	350110.82
B97	321546.04	350148.21

PLAN DE LOTISSEMENT

TABLEAU QUANTITATIF

IMMEUBLE	Nbr MAGASIN	Nbr Appt au RDC	Nbr Appt PAR ETAGE	TOTAL MAGASIN PAR IMMEUBLE	TOTAL APPARTEMENTS PAR IMMEUBLE
A	3	0	4	3	12
B	3	4	7	3	25
C	0	10	9	0	37
D	0	4	4	0	16
E	0	9	11	0	42
F	3	3	9	3	30
TOTAL	9	30	44	9	162

NOMBRE DE PLACE DE PARKING AU SOUS SOL 230 PLACES

SURFACE CONSTRUITE

NIVEAUX	SURFACE CONSTRUITE
SOUS SOL	7500 m²
REZ DE CHAUSSEE	4080 m²
1er ETAGE	3400m²
2éme ETAGE	3400m²
3éme ETAGE	3400m²
TOTAL	21780m²

SURFACE TERRAIN 11841 m²

SURFACE CONSTRUITE AU SOL 4080 m²

SURFACE PLANCHERS SANS SOUS SOL 14280m²